Government of Rajasthan
REGISTRATION & STAMPS DEPARTMENT, RAJASTHAN, AJMER
SUB-REGISTRAR : KOTA-I

Fee Receipt
Appendix I-Form No. 9 (Rule 75 & 131) Print Date : 02-07-2021 1:19 PM

Fee Receipt No	:	202102123005346	Receipt Date	:	02/07/2021
Name	:	SHUBHAM GREEN COLONIZERS PVT LTD TH ARUN MEHTA ,	Document S. No.	:	202101123005017
Address	:	FLAT No.810 ,ARAWALI TOWER CITY CENTER HAIGHTS ,KOTA ,KOTA			
Document Type	:	Township Policy-2010			
Face Value	:	₹ 26531	Evaluated Value	:	₹ 1213260

Ord-Registration Fee	:	₹ 1062	Fee for Memorandum Us_64_67	:	₹
CSI	:	₹ 300	Certified copying fees Us_57	:	₹ 0
Stamp (Memorandum)	:	₹	Reg (memorandum)	:	₹
Surcharge	:	₹ 1911	Stamp Duty	:	₹ 6368
Penalty	:	₹ 0	Inspection fee	:	₹ 0
Us_25_34	:	₹ 0	Commission	:	₹ 0
Custody	:	₹	Others	:	₹ 0
			Cash Amount Received	:	**₹ 0**
			Other than Cash	:	**₹ 9641**
			Total Amount	:	**₹ 9641**

Mode of Payment (#Mode Number Amount #)
e-Gras Challan 51089790 ₹ 9641

Signature of presenter or applicant for copy or Search certificate

Signature of recipient and date of return receipt

Cashier

SUB-REGISTRAR

Presentation Endorsement

आज दिनांक 02 माह 07 सन् 2021 को 01:15 PM बजे
श्री/श्रीमती/सुश्री SHUBHAM GREEN COLONIZERS PVT LTD TH ARUN MEHTA पुत्र/पुत्री/पत्नि श्री DR JHAMAN DAS
उम्र 44 वर्ष, जाति 0-SINDHI , व्यवसाय Business
निवासी House No.:FLAT No.810, Colony: ARAWALI TOWER CITY CENTER HAIGHTS , Area: BAJRANG NAGAR , City: KOTA , Pin code: 324001, District: KOTA, State: RAJASTHAN
ने मेरे सम्मुख दस्तावेज पंजीयन हेतु प्रस्तुत किया ।

हस्ताक्षर प्रस्तुतकर्ता
202101123005017

हस्ताक्षर उप पंजीयक,
KOTA-I

The lease deed issued/executed under the Rajasthan Township Policy-2010,- (i) in case of first allotment of plot for residential, institutional, industrial, tourism unit, etc.

Fees Receipt Endorsement

रसीद नं.	202102123005346
दिनांक	02-07-2021
पंजीयन शुल्क ₹	1062
प्रतिलिपि शुल्क ₹	0
पृष्ठांकन शुल्क ₹	300
अन्य शुल्क ₹	0
कमी स्टाम्प शुल्क ₹	6368
कमी सरचार्ज शुल्क ₹	1911
कुल योग	9641

202101123005017

उप पंजीयक, KOTA-I

The lease deed issued/executed under the Rajasthan Township Policy-2010,- (i) in case of first allotment of plot for residential, institutional, industrial, tourism unit, etc.

Endorsement of Execution

अनु क्र.	पक्षकारों का नाम व पता	छायाचित्र	अंगूठा	पक्षकारों का प्रकार
1	श्री/श्रीमती/सुश्री UIT KOTA , पुत्र/पुत्री/पत्नि श्री SEC.UIT KOTA , व्यवसाय जाति Nagar Sudhar Nyas			Executant Age : 0 Signature :
2	श्री/श्रीमती/सुश्री SHUBHAM GREEN COLONIZERS PVT LTD TH ARUN MEHTA , पुत्र/पुत्री/पत्नि श्री DR JHAMAN DAS , व्यवसाय Businessजाति 0-SINDHI House No.:FLAT No.810, Colony: ARAWALI TOWER CITY CENTER HAIGHTS , Area: BAJRANG NAGAR , City: KOTA , Pin code: 324001, District: KOTA, State: RAJASTHAN			Claimant Age : 44 Signature :

ने लेख्यपत्र The lease deed issued/executed under the Rajasthan Township Policy-2010,- (i) in case of first allotment of plot for residential, institutional, industrial, tourism unit, etc. को पढ़ सुन व समझकर निष्पादन करना स्वीकार किया ।

प्रतिफल राशि रू 26531/- पूर्व में / मेरे समक्ष / में से रू 26531/- पूर्व में _____ ये मेरे समक्ष प्राप्त करना स्वीकार किया ।

उक्त निष्पादन कर्ता की पहचान निम्न व्यक्तियों ने की है जिनके हस्ताक्षर एवं अंगूठा निशान मेरे समक्ष लिए गए है।

अनु क्र.	गवाहों का नाम व पता	छायाचित्र	अंगूठा	हस्ताक्षर
1	Name: श्री/श्रीमती/सुश्री MAHAVEER PRASAD SHARMA , पुत्र/पुत्री/पत्नि श्री GOPAL LAL जाति BRAHMIN Age: 69 Add: House No.:32, Colony: AADARSH NAGAR , Area: BUNDI ROAD, City: KOTA, Pin code: 324008, District: KOTA, State: RAJASTHAN			Signature
2	Name: श्री/श्रीमती/सुश्री BHUPENDAR KUMAR , पुत्र/पुत्री/पत्नि श्री RAMNARAYAN MEHRA जाति MEHRA Age: 41 Add: House No.:1092, Colony: VINOBA BHAVA NAGAR , Area: VINOBA BHAVA NAGAR , City: KOTA , Pin code: 324005, District: KOTA, State: RAJASTHAN			Signature

202101123005017

उप पंजीयक, KOTA-I

The lease deed issued/executed under the Rajasthan Township Policy-2010,- (i) in case of first allotment of plot for residential, institutional, industrial, tourism unit, etc.

Registration Endorsement

आज दिनांक 02/07/2021 को
पुस्तक संख्या 1 जिल्द संख्या 1530 में
पृष्ठ संख्या 103 क्रम संख्या 202103123103447 पर पंजीबद्ध किया गया तथा
अतिरिक्त पुस्तक संख्या 1 जिल्द संख्या 4431 के
पृष्ठ संख्या 75 से 82 पर चस्पा किया गया ।

202101123005017

उप पंजीयक, KOTA-I

The lease deed issued/executed under the Rajasthan Township Policy-2010,- (i) in case of first allotment of plot for residential, institutional, industrial, tourism unit, etc.

नगर विकास न्यास, कोटा

Lancerti

प्रमाण पत्र

क्रमांक :- 203 दिनांक 30/6/2021

1. भूस्वामी का नाम श्रीश्री 66 प्रा.लि. पंजी. कार्या. चौधरी होटल परिसर, माडल पेट्रोल पंप
2. पिता / पति का नाम के सामने, रोडवेज सर्किल के पास, कोटा (राज.) जरिये निदेशक अरुण मेहता S/o श्री भगवानदास मेहता
3. भूखण्ड संख्या : सी-24
4. योजना का नाम /ग्राम का नाम : सिटीफोन सिटी (नयाबेड़ा)
5. क्षेत्रफल : 162.22 वर्ग गज
6 वार्षिक नगरीय कर की राशि : –
7 एक बारीय नगरीय कर की राशि : 21,225/-

(कालम 6 से 10 गुणा राशि)

उपरोक्त राशि अक्षरे रुपये इक्कीस हजार दो सौ पच्चीस रुपये मात्र

रसीद/चालान नम्बर 1583 दिनांक 23/09/20 द्वारा जमा कराये गये।

अतः भू आवंटन की शर्त संख्या / 2 (ब) / में अंकित अवधि को अवशेष अवधि के लिए

/ नगरीय कर के भुगतान से उक्त भूखण्ड को मुक्त किया जाता है।

उपसचिव एवं प्राधिकृत अधिकारी
नगर विकास न्यास, कोटा

प्राधिकृत अधिकारी (उपसचिव) नगर विकास न्यास, कोटा

[illegible]

[illegible]

[illegible]

[illegible]

[illegible]

[illegible]

[illegible]

[illegible]

[illegible]

[illegible]

नगर विकास न्यास, कोटा

Land_8

भू-आवंटन पत्र

राजस्थान भू-राजस्व अधिनियम 1956 की धारा 90 (क) के तहत पुनः आवंटन

क्रमांक : 203 दिनांक: 30/6/2021

(1) भूखण्ड धारी का नाम : शुभश्री कॉलो० प्रा० लि० पंजी० कार्या० चौधरी होटल परिसर, मॉडर्न पेट्रोल पंप के सामने, एरोड्राम सर्किल के पास, कोटा (राज०) और निदेशक अरुण मेहता S/o श्री झामनदास मेहता, नि० फ्लेट सं० 810, अरावली टावर, सिटी सेन्टर हाईट्स, बजरंग नगर, कोटा (राज०)

(4) भूखण्ड संख्या : सी-24 क्षेत्रफल 162.22 वर्ग गज

(5) योजना का नाम : सिलिकॉन सिटी (नयाखेड़ा)

(6) सहकारी समिति का नाम :

(7) जोन संख्या :

राज्य सरकार के आदेश क्रमांक प.5 (3) न.वि.वि. /3/99 दिनांक 10/07/99 व प.3 (90) न.वि.वि./3/2012 जयपुर दिनांक 21/06/2012 आवासीय/वाणिज्यक उपयोग हेतु नियमित कर नियमन दर पर पुनः आवंटित किया जाता है। आवंटन की शर्तें निम्न प्रकार होगीः-

1. यह आवंटन 99 वर्ष की लीज पर किया जाता है ।
2. यह भूखण्ड पर नियमानुसार नगरीय कर देय होगा जो कि वर्तमान में उस क्षेत्र की नियमन दर/आरक्षित दर का 2.5% 50% प्रति वर्ग गज है नगरीय कर की उक्त राशि की नियमानुसार समय-समय पर बढ़ोत्तरी की जा सकेगी।
3. भवन निर्माण का कार्य आवंटन पत्र जारी होने की तिथि से 5 वर्ष की अवधि में पूर्ण करना होगा।
4. यदि भूखण्ड 500 वर्ग मी. क्षेत्र तक का है, तो उस पर निर्माण इस आवंटन पत्र के आधार पर किया जा सकता है। जिसमें साइट प्लान के अनुसार सेट बैंक छोड़ने होंगे एवं न्यास के बिल्डिंग बाइलाज के अनुसार निर्माण किया जा सकेगा, इसके लिए भूखण्ड धारक द्वारा प्रस्तावित निर्माण के लिए निर्धारित आवंटन पत्र आवश्यक दस्तावेजों के साथ सक्षम अधिकारी को प्रस्तुत किया जाना आवश्यक होगा।
5. इस आवंटन पत्र के आधार पर उक्त भूखण्ड के सरकार/ जीवन बीमा निगम/शिडयूल्ड बैंक/ सरकारी ऋणदात्री संस्था/ एचण्डीण्एफण्सीण् अथवा नेशनल हाऊसिंग बैंक द्वारा अधिकृत ऋणदात्री संस्थाओं के पास भवन निर्माण के ऋण के लिए गिरवी रखा जा सकेगा।
6. साइट प्लान न्यास द्वारा अनुमोदित ले आउट प्लान के अनुसार जारी किया गया है।
7. आवंटी द्वारा सम्बन्धित नियमों, उपनियमों, राज्य सरकार/न्यास के समय-समय पर जारी होने वाले निर्देशों, निर्णयों की अनुपालना की जाएगी।
8. प्रार्थी के आवेदन अनुसार भूखण्ड पर प्रार्थी का कब्जा निर्विवाद मानकर यह आवंटन पत्र जारी किया जा रहा है। अतः कब्जा सम्बन्धित किसी प्रकार के विवाद के लिए न्यास जिम्मेदार नहीं होगा।
9. आवंटी द्वारा भूखण्ड विक्रय करने पर क्रेता द्वारा भूखण्ड का हस्तान्तरण नगर विकास न्यास के नियमों के अनुसार न्यास से करवाना होगा।
10. यह आवंटन पत्र भूखण्ड के आवासीय /वाणिज्यिक प्रयोजनार्थ है। निर्मित भूखण्ड के सम्बन्ध में राज्य सरकार के आदेश दिनांक प.5 (3) न.वि.वि. /3/99 दिनांक 10/07/99 प.3 (90) न.वि.वि./3/2012 जयपुर दिनांक 21/06/2012 द्वारा भवन वाणिज्यिक विनियमों के प्रवाधानों में प्रदत्त शिथिलता के तहत नियमन योग्य निर्माण ही नियमित किया जाता है तथा नियमन आयोग्य निर्माण के संबंध में संबंधित विनियमों के अनुसार कार्यवाही की जायेगी।
11. उपरोक्तशर्तों में से किसी भी शर्त के उल्लंघन किये जाने पर उक्त आवंटन निरस्त किया जा सकेगा।
12. भूखण्ड की लीज डीड का नियमानुसार पंजीयन करवाया जाना अनिवार्य होगा।

भूखण्ड का विवरण निम्नानुसार है :-

भूखण्ड कि लम्बाई X चौड़ाई

सामने (	25'	)	पीछे (	48'	)
साइड (	40'	)	(	40'	) वर्ग गज 162.22 व.ग.

अधिकतम एफ.ए.आर. स्वीकार्य .....

भवन की अधिकतम स्वीकार्य ऊँचाई .....

सहायक नगर नियोजक
नगर विकास न्यास, कोटा

प्राधिकृत अधिकारी (विशेषाधिकारी)
नगर विकास न्यास, कोटा

दिनांक : .....

क्रमांकः-

प्रतिलिपि : लेखा शाखा नगर विकास न्यास, कोटा को सूचनार्थ एंव नगरीय कर रजिस्टर तुरंत तैयार करने हेतु।

प्राधिकृत अधिकारी (विशेषाधिकारी)
नगर विकास न्यास, कोटा

प्राधिकृत अधिकारी (उपसचिव)
नगर विकास न्यास कोटा

नगर विकास न्यास, कोटा

Rul22

राजस्थान नगरीय क्षेत्र (कृषि भूमि का गैर-कृषिक प्रयोजन के लिए उपयोग की अनुज्ञा और नियम, 2012 के नियम 22 के अन्तर्गत भूमि का पट्टा विलेख

क्रमांक : 209 दिनांक: 30/6/21

यह विलेख आज वर्ष 2021 के माह 06 के 30 वे दिन / नगर सुधार न्यास, कोटा (जिन्हें इसके बाद नगर निकाय कहकर संबोधित किया गया है) प्रथम पक्ष एवं श्री श्रमश्रीन कॉलो० प्रा० लि० पंजी० कार्या० जयपुर पुत्र श्री ..... जाति ..... व्यवसाय..... निवासी होटल परिसर गॉर्डन पेट्रोल पंप के सामने, एरोड्राम सर्किल के पास, कोटा जरिये निदेशक अरुण मेहता S/o श्री ओमप्रकाश मेहता फ्लेट सं० 810, अरावली गार्डन सिटी सेन्टर - हाईवेस, बजरंग नगर, कोटा (राज०) (जिनको इसके बाद लीजधारक संबोधित किया गया है) द्वितीय पक्ष तथा इस इबारत में जहां कहीं प्रसंग से वैसा अर्थ निकले, उनके उत्तराधिकारी, निर्वाहक, प्रबंधक प्रतिनिधि और मुन्तकिल अलैह भी सममिलित होंगे) के मध्य निष्पादित हुआ है।

यह विलेख साक्ष्यांकित करता है कि प्रीमियम तथा विकास शुल्क की रकम जो लीजधारक(पट्टाधारक) के द्वारा अदा कर दी गई है और जिसकी रसीद नगर निकाय के द्वारा स्वीकार कर ली गई है, ओर इसमें उल्लेखित शर्तो और करारों जो लीजधारक द्वारा निष्पादित तथा पालन किये जायेंगे, के एवज में नगर निकाय इनके द्वारा लीजधारक को जमीन का वह तमाम भूखण्ड (जिसे इसके बाद उक्त भूखण्ड कहकर संबोधित किया गया है) प्रदान और लीज करती है जो योजना सिलिकोन सिटी ..... राजस्व ग्राम नमाखेड़ा ..... के खसरा संख्या 119/1 ..... क्षेत्रफल 162.22 व.गज ..... में स्थित है और जो अपनी सीमा और क्षेत्रफल के साथ इसके अन्तर्गत लिखे गये परिशिष्ट में अधिक पूर्णरूपेण वर्णित है तथा जिसका आकार विशेष रूप से इससे संलग्न नक्शे में लाल रंग में दिखाया गया है ओर जिसे पूर्ण स्वामित्व संबंधी स्वत्वों सहित किन्तु निम्नलिखित तमाम व प्रत्येक अपवादों संरक्षणों, प्रतिबंधों, बंधनों, शर्ते और करारों के अधीन खरीददार अपने उपयोग, उपभोग ओर इस्तेमाल के लिए अपने अधिकार में रखेगा अर्थात:-

1 लीजधारक नगर निकाय क कार्यालय में या ऐसे स्थान पर जिसे नगर निकाय समय-समय पर इस हेतु नियत कर दें प्रयेक वर्ष अप्रैल के प्रथम दिन उक्त भूखण्ड के संबंध में उक्त नियमों के नियम 20 के उप-नियम(1) के अन्तर्गत निर्धारित किये गये नगरीय निर्धारण (शहरी जमाबन्दी या भूमि का किराया) के तौर पर रूपये इकतीस हजार पांच सौ इकतीस रुपये मात्र ..... अंके 31,531/- ..... मात्र पेशगी अदा करेगा, परन्तु लीजधारक,यदि चाहे तो, एक बारीय नगरीय निर्धारण (शहरी जमाबन्दी या भूमि का किराया)की राशि जमा करा सकेगा, जो उस वर्ष, जिसमें राशि जमा करायी जाती है, को सम्मिलित करते हुए, पूर्ण वार्षिक नगरीय निधारण की राशि के आठ गुणा के बराबर होगी और इस प्रकार जमा कराई गयी नगरीय निर्धारण की राशि के फलस्वरूप लीजधारक उक्त भूखण्ड पर नगरीय निर्धारण की राशि के संदाय के दायित्व से छूट प्राप्त करने का अधिकारी होगा।

2 एक बार नियत किया गया नगरीय निर्धारण या भूमि का किराया प्रत्येक 15 वर्ष के पश्चात् और विक्रय या दान या अन्यथा द्वारा ऐसे अन्तरण पर भी पुनरीक्षण का दायी होगा और ऐसी वृद्धि प्रत्येक अवसर पर ऐसे पुनरीक्षण या यथास्थिति, अन्तरण के समय नगरीय निर्धारण या भूमि के किराये का 25 प्रतिशत होगी।

3 पट्टे की अवधि : - पट्टाधृति अधिकार 99 वर्ष के लिए होंगे।

4 उक्त भूखण्ड का उपयोग केवल आवासीय ..... प्रयोजन, जिसके लिए नगर निकाय द्वारा उक्त नियमों के अन्तर्गत अनुमाति दी गयी है, के लिए किया जाऐगा और इसी प्रयोजन के उपयेग हेतु इस भूखण्ड पर भवन का निर्माण किया जायेगा।

5 इस पट्टा विलेख की तारीख से 7 वर्ष या ऐसी अतिरिक्त अवधि के भीतर जो नियम 26 के अन्तर्गत बढा दी जावें, लीजधारक के द्वारा इस भूखण्ड पर भवन का निर्माण कराया जायेगा।

6 लीजधारक उक्त भूखण्ड को आगे और अन्तरित या उप-पट्टे पर दे सकेगा। उक्त नियमों में अन्तर्विष्ट निबंधन और शर्ते ओर अन्य उपबंध यथावश्यक परिवर्तन सहित,अन्तरिती या उप पट्टेदार पर इस प्रकार लागू होंगे मानो प्रश्नगत उक्त भूखण्ड नगर निकाय द्वारा दिया गया है या अन्तरित किया गया है लीजधारक द्वारा उप-पट्टे की कालावधि स्वयं द्वारा अवधारित की जायेगी किन्तु किसी भी दशा में मूल पट्टे की और शर्तो या किन्हीं पृथक आदेशों द्वारा जो राज्य सरकार द्वारा समय-समय पर इस निमित्त विनिर्दिष्ट मामलों मे जारी किये जायें शासित होगें।

7 उक्त भूखण्ड के अन्तरण के मामले में, अन्तरिती के पक्ष में नाम में अन्तरण के लिये नगर निकाय को आवेदन के साथ

उप पंजीयक कोटा (प्रथम)

रजिस्ट्रीकृत विक्रय विलेख, दान विलेख, या वसीयत या अन्य सुसंगत दस्तावेज प्रस्तुत किये जायेंगे। प्रत्येक अन्तरण के लिए आवेदन के साथ दस रूपये प्रति वर्गमीरटर की दर से अन्तरण फीस निक्षिप्त की जायेगी। परन्तु लीजधारक की मृत्यु के मामलों में इस नियम के अधीन कोई फीस प्रभारित नहीं की जायेगी।

8 उक्त नियमों के अधीन किसी व्यक्ति के प्रति परादेय प्रीमियम या नगरीय निर्धारण या ब्याज, आन्तरिक/ बाह्य विकास प्रभारों का कोई बकाया राजस्थान भू-राजस्व अधिनियम 1956 के अधीन भू-राजस्व की बकाया के रूप में लीजधारक से वसूलीय होगा।

9 यदि आबंटन या पट्टा विलेख के निष्पादन के पश्चात् यह पाया जाता है कि आबंटन या पट्टा विलेख की दुरभिसंधि या उसके उल्लंघन के कपटपूर्ण दस्तावेज के आधार पर दुर्व्यपदेशन द्वारा अभिप्राप्त किया गया है या आबंटन या पट्टा विलेख के निबंधनों और शर्तों का अतिक्रमण किया गया है तो नगर निकाय उक्त भूखण्ड पर उसके किसी सन्निर्माण सहित उसे प्रतिसंहृत करेगा जो सभी प्रभारों से रहित नगर निकाय में निहित समझे जायेंगे, और नगर निकाय किसी भी व्यक्ति को कारित किसी भी प्रकार की नुकसानी के लिए दायी नहीं होगा।

10 इस पट्टा विलेख के आधार पर उक्त भूखण्ड को सरकार/ जीवन बीमा निगम/शिड्यूल्ड बैंक/ सरकार ऋणदात्री संस्था/ एच.डी. एफ.सी अथवा नेशनल बैंक द्वारा अधिकृत ऋणदात्री संस्थाओं के पास भवन निर्माण के ऋण के लिए बंधक रखा जा सकेगा।

:: परिशिष्ट ::

कस्बे का नाम .....
राजस्व ग्राम .....नयाखेड़ा.....
खसरा नम्बर .....119/1.....
योजना का नाम .....सिल्वर सिटी.....
विस्तृत नाम सहित क्षेत्रफल वर्ग गज/ मीटर ...162.22 व.ग. $\frac{25+48'}{2} \times 40' = 1460$ व.गु.

पूर्व ...सी.-22... पश्चिम .....रोड..... भूखण्ड की संख्या यदि कोई हो ...सी-24... सीमा उत्तर ...सी-25... दक्षिण ...रोड व अन्य आराजी मानचित्र संलग्न है

इसके साक्षी के रूपमें इसके फरीकेन ने इसके बाद प्रत्येक दशा में निर्देशित स्थानों और तारीखों पर अपने अपने हस्ताक्षर कर दिये है

नगरीय निकाय की ओर से

आज सन् 20..... के माह ..... के ..... वें दिन श्री ..... ने निम्न की उपस्थिति में (स्थान) में हस्ताक्षर किये:

नगरीय निकाय -प्रथम पक्ष
(सक्षम अधिकारी के हस्ताक्षर एवं मोहर)

साक्षी:-

1 नाम : .....शाहब खान.....
पुत्र : श्री .....रफीकउद्दीन.....
व्यवसाय : ....पटवारी पा.ग.कोटा
निवास स्थान : .....कोटा (राज.)

.....
साक्षी

2 नाम : .....
पुत्र : श्री .....
व्यवसाय : .....
निवास स्थान : .....

.....
साक्षी

आज सन् 20..... के माह ..... के ..... वें दिन को निम्नलिखित में उक्त श्री ..... लीजधारक द्वारा कार्यालय ..... में हस्ताक्षर किये गये।

.....
लीजधारक -द्वितीय पक्ष

साक्षी:-

1 नाम : .....प्रतीक्ष.....
पुत्र : श्री .....महावीर कुमार.....
व्यवसाय : .....
निवास स्थान : .....दिव्यांश सिटी कोटा

.....
साक्षी

2 नाम : .....महेश.....
पुत्र : श्री .....खुशीलाल.....
व्यवसाय : .....
निवास स्थान : .....रामपुरा कोटा

.....
साक्षी

RESIDENTIAL SITE PLAN OF PLOT IN " SILICON CITY "

VILLAGE:- NAYA KHERA TEHSIL :- LADPURA DISST.:-KOTA

KH.NO.- 119 / 1

OWNER :- शुभम् ग्रीन कॉलोनाइजर्स प्रा. लि.पंजीकृत कार्यालय चौधरी होटल परिसर,मॉडन पेट्रोल पम्प के सामने एरोड्रम सर्किल के पास,कोटा (राज.) जरिये निदेशक
अरूण मेहता आत्मज डॉ श्री झामन दास मेहता निवासी–फ्लेट संख्या 810,अरावली टावर सिटी सेन्टर हाईट्स,बजरंग नगर, कोटा (राज.)

PLOT NO.:- C-24

PLOT AREA:- (25'+ 48')/2 X 40'= 1460.00 SQ.FT. 162.22 SQ.YD.

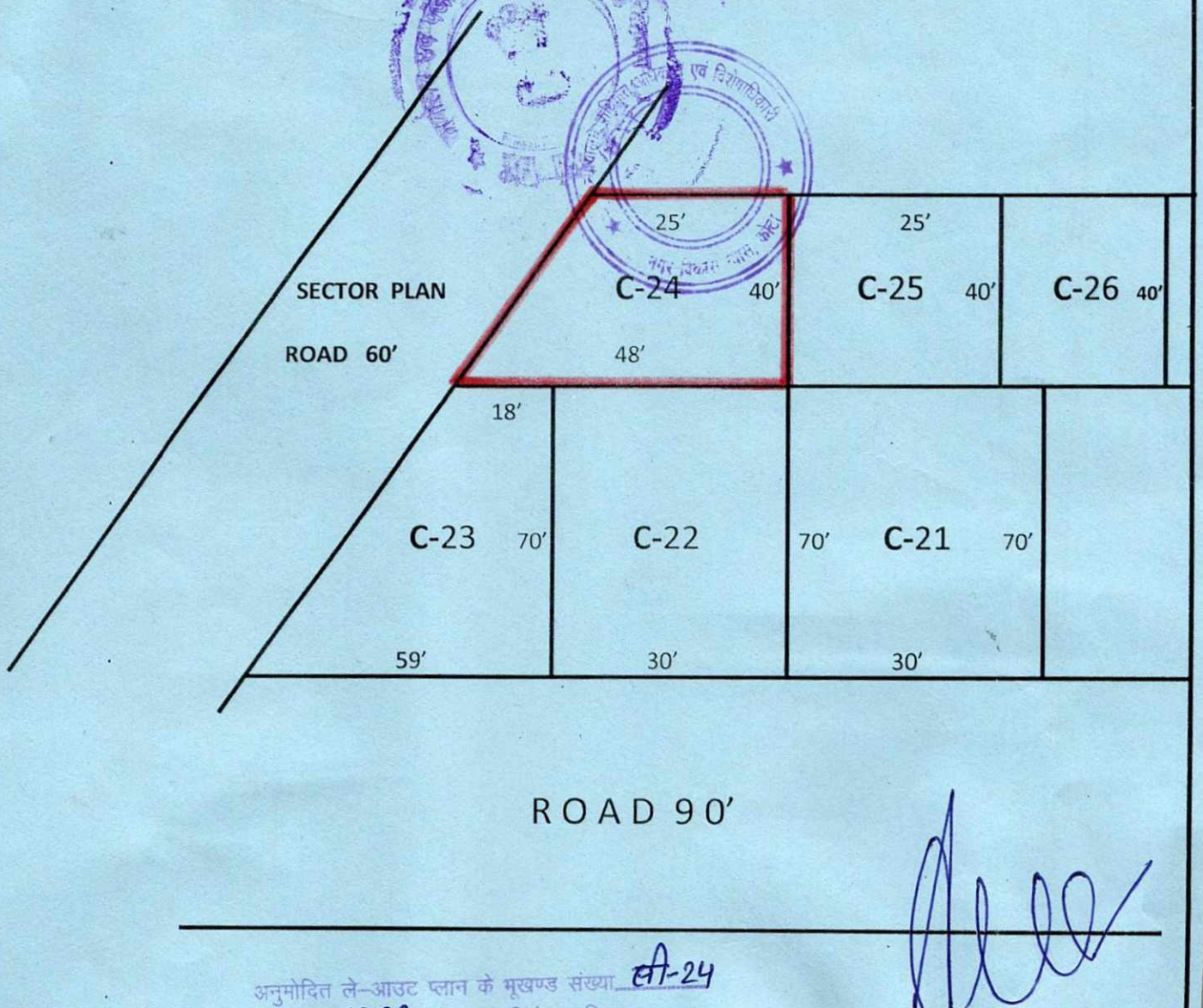

अनुमोदित ले–आउट प्लान के भूखण्ड संख्या सी-24
क्षेत्रफल 162.22 वर्गगज के लिये प्रमाणित

पटवारी, भू–अभिलेख निरीक्षक, तहसीलदार, प्राधिकृत अधिकारी उप पंजीयक

Sig.of owner

Registration Endorsement

आज दिनांक 02/07/2021 को
पुस्तक संख्या 1 जिल्द संख्या 1530 में
पृष्ठ संख्या 103 क्रम संख्या 202103123103447 पर पंजीबद्ध किया गया तथा
अतिरिक्त पुस्तक संख्या 1 जिल्द संख्या 4431 के
पृष्ठ संख्या 75 से 82 पर चस्पा किया गया ।

202101123005017

उप पंजीयक, KOTA-I

The lease deed issued/executed under the Rajasthan Township Policy-2010,- (i) in case of first allotment of plot for residential, institutional, industrial, tourism unit, etc.